GIS2BIM OpenAnalysis

Locatie Rapport

TOP10NL

Tekening	1 / 5
Adres	Grote Kerk, Dordrecht
Gemeente	Dordrecht
Lat/Lng	51.81330, 4.66010
Schaal	1:2.500
Formaat	A3 liggend
Datum	14-01-2026

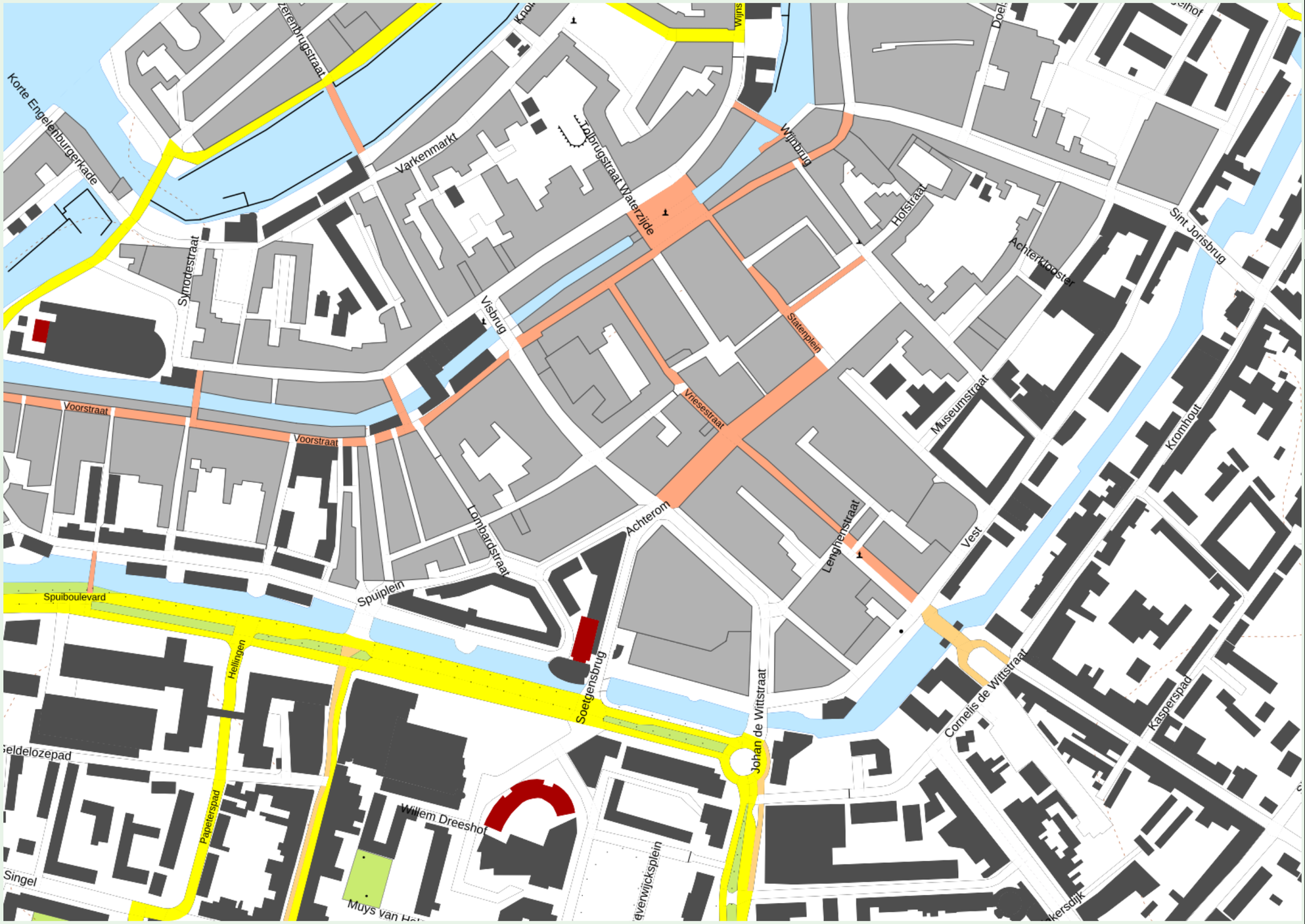

Legenda

- Groenvoorziening
- Water
- Bebouwd gebied
- Verharding
- Locatie marker

GIS2BIM

OpenAEC Foundation

www.openaec.org

GIS2BIM OpenAnalysis

Locatie Rapport

Luchtfoto

Tekening	2 / 5
Adres	Grote Kerk, Dordrecht
Gemeente	Dordrecht
Lat/Lng	51.81330, 4.66010
Schaal	1:2.500
Formaat	A3 liggend
Datum	14-01-2026

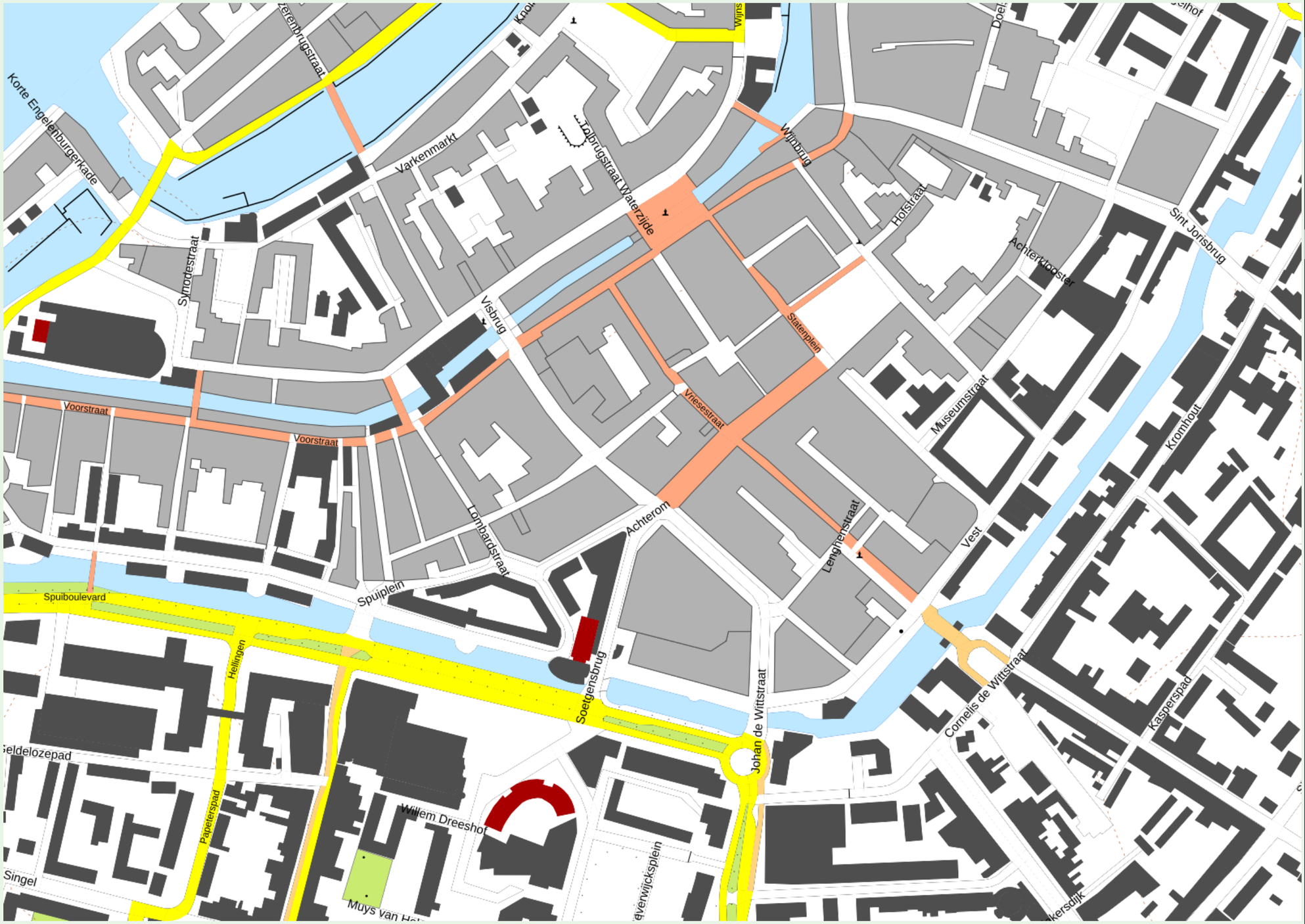

Legenda

- Groenvoorziening
- Water
- Bebouwd gebied
- Verharding
- Locatie marker

GIS2BIM

OpenAEC Foundation

www.openaec.org

GIS2BIM OpenAnalysis

Locatie Rapport

Kadaster

Tekening	3 / 5
Adres	Grote Kerk, Dordrecht
Gemeente	Dordrecht
Lat/Lng	51.81330, 4.66010
Schaal	1:1.000
Formaat	A3 liggend
Datum	14-01-2026

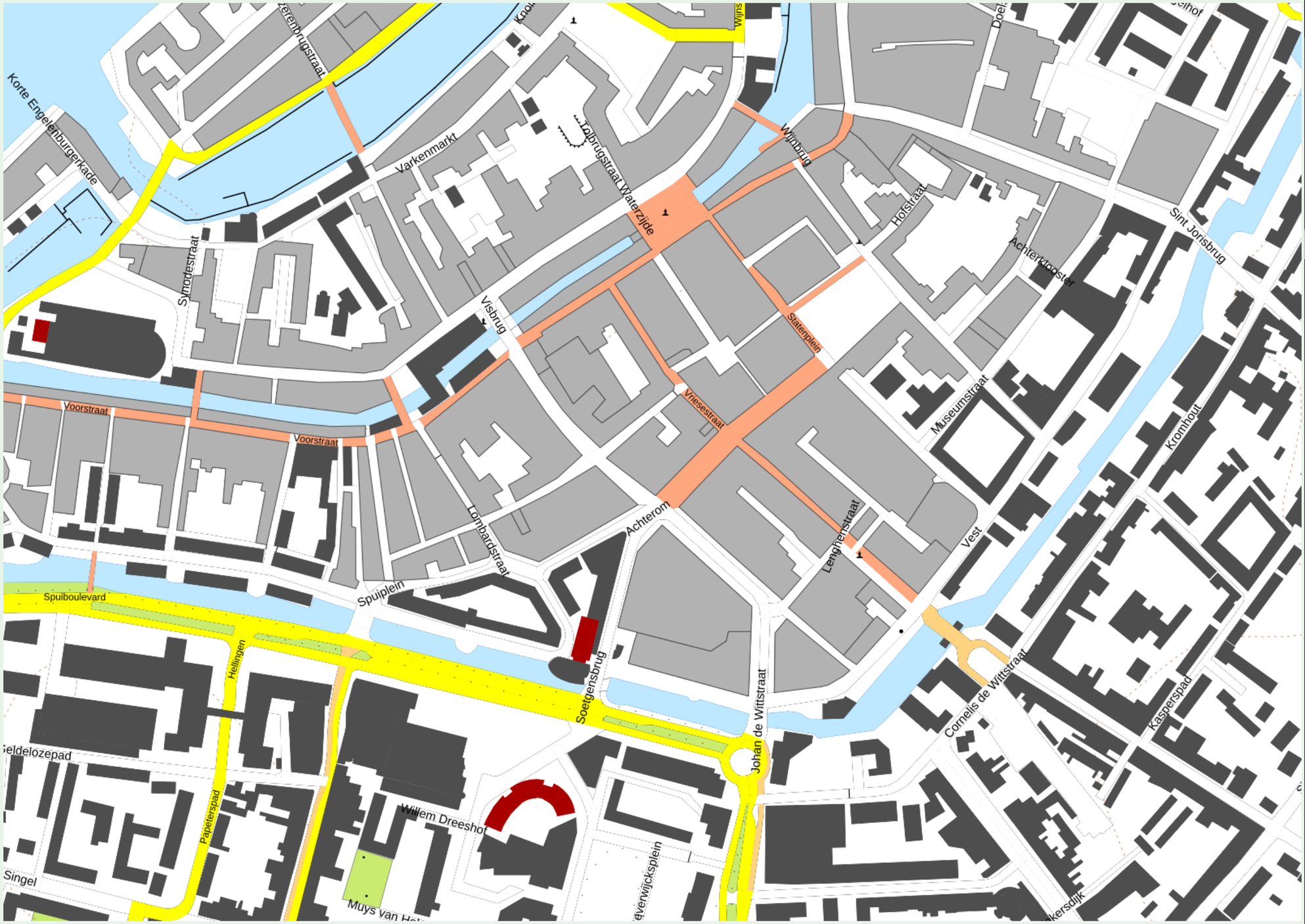

Legenda

- Groenvoorziening
- Water
- Bebouwd gebied
- Verharding
- Locatie marker

GIS2BIM

OpenAEC Foundation

www.openaec.org

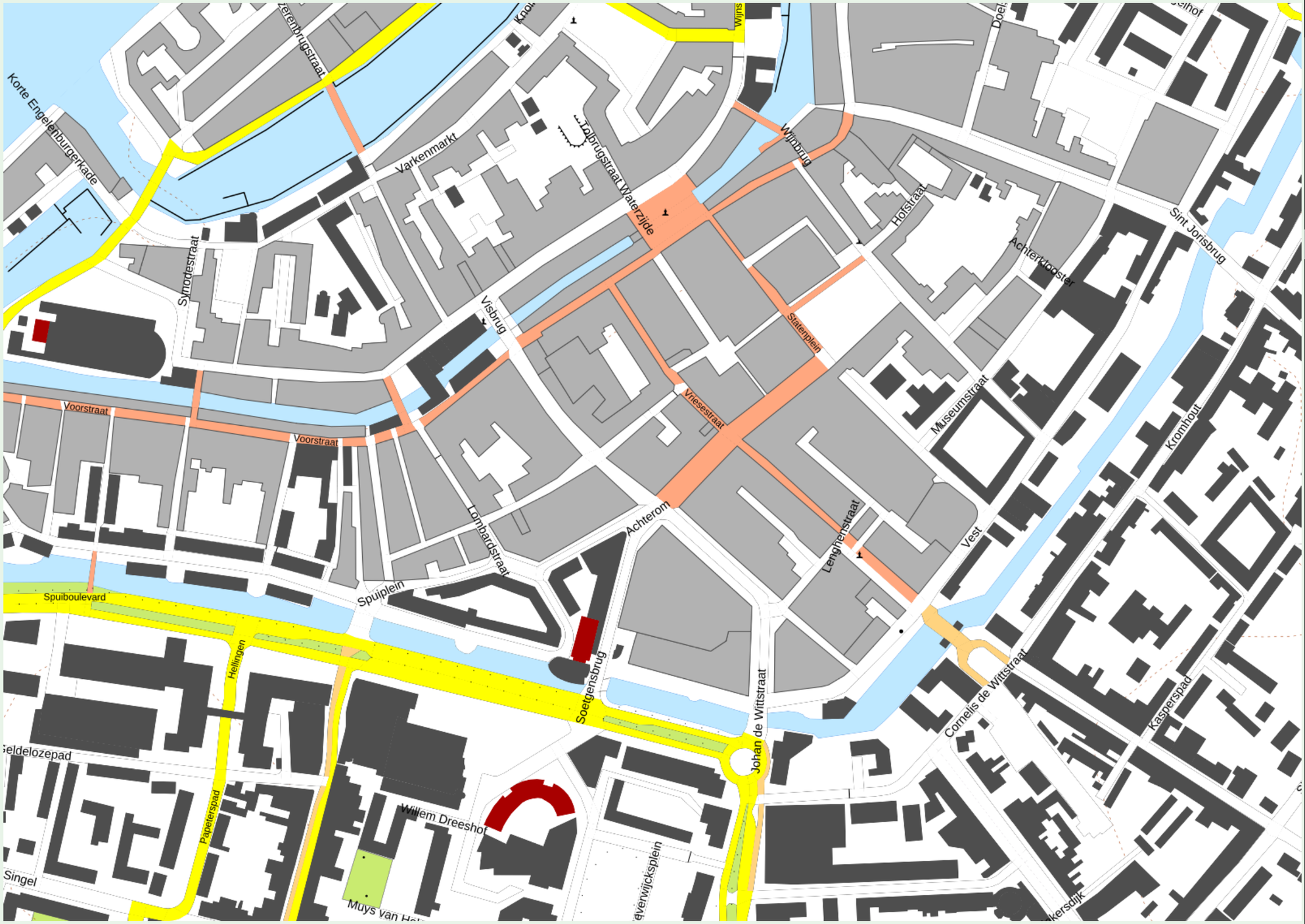

0m 20m 40m 60m 80m

GIS2BIM OpenAnalysis

Locatie Rapport

BAG Panden

Tekening	4 / 5
Adres	Grote Kerk, Dordrecht
Gemeente	Dordrecht
Lat/Lng	51.81330, 4.66010
Schaal	1:1.000
Formaat	A3 liggend
Datum	14-01-2026

Legenda

- Groenvoorziening
- Water
- Bebouwd gebied
- Verharding
- Locatie marker

GIS2BIM

OpenAEC Foundation

www.openaec.org

GIS2BIM OpenAnalysis

Locatie Rapport

Bestemmingsplan

Tekening	5 / 5
Adres	Grote Kerk, Dordrecht
Gemeente	Dordrecht
Lat/Lng	51.81330, 4.66010
Schaal	1:2.500
Formaat	A3 liggend
Datum	14-01-2026

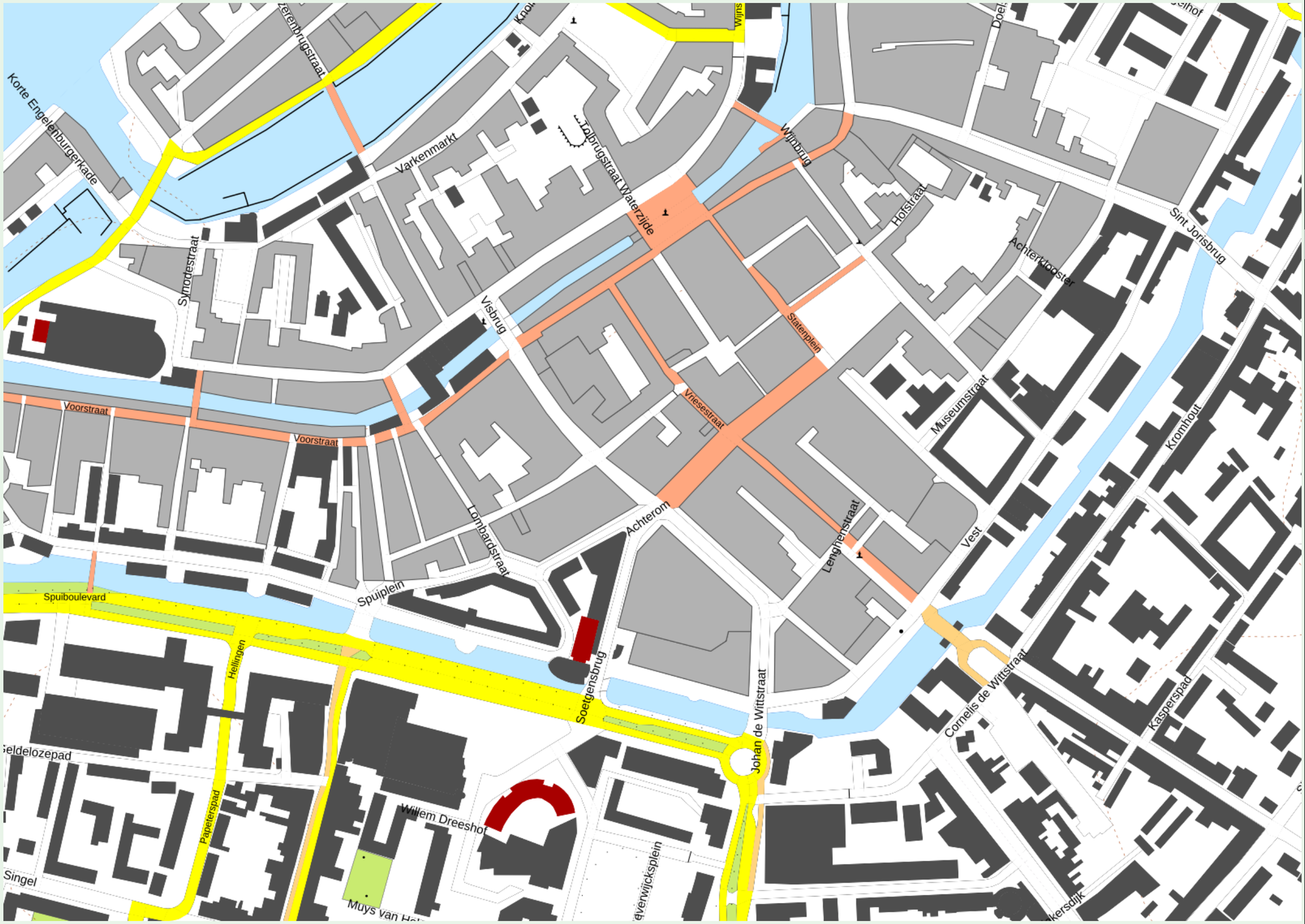

Legenda

- Groenvoorziening
- Water
- Bebouwd gebied
- Verharding
- Locatie marker

GIS2BIM

OpenAEC Foundation

www.openaec.org